Clustering v4 — Bâti récent

Bordeaux Métropole — Constructions 2016-2023

7087 bâtiments — résidentiel individuel, nb_logements < 4, année >= 2016

Algorithme : KMeans k=10 — 11 features — Source : BDNB 2025-07-a — mars 2026

Ce rapport analyse les typologies du bâti résidentiel individuel récent (moins de 10 ans) sur Bordeaux Métropole. Les cartes interactives sont disponibles sur la carte web associée.

Profil synthétique des 10 clusters

Cl.	Nom	N	%	Surf.	Haut.	Niv.	Année	Mat. murs
0	Maison R+1 / 91m² / 6m / 2017 /	1587	22.4	91	6.0	2	2017	BRIQUES
1	Pavillon / 118m² / 3m / 2021 / b	1484	20.9	118	3.0	1	2021	BRIQUES
2	Maison R+1 / 250m² / 5m / 2020	14	0.2	250	5.0	1	2020	INDETERMINE
3	Maison R+1 / 156m² / 6m / 2019 /	326	4.6	156	6.0	2	2019	BRIQUES
4	Maison R+1 / 84m² / 6m / 2021 /	875	12.3	84	6.0	2	2021	BRIQUES
5	Maison R+1 / 74m² / 6m / 2019 /	772	10.9	74	6.0	2	2019	BETON
6	Grande maison / 449m² / 4m / 201	6	0.1	449	4.0	1	2019	BRIQUES
7	Pavillon / 151m² / 4m / 2017 / b	1292	18.2	151	4.0	1	2017	BRIQUES
8	Maison R+1 / 94m² / 6m / 2019 /	572	8.1	94	6.0	1	2019	BRIQUES
9	Pavillon / 162m² / 4m / 2020 / b	159	2.2	162	4.0	1	2020	BRIQUES

1. Effectifs par cluster

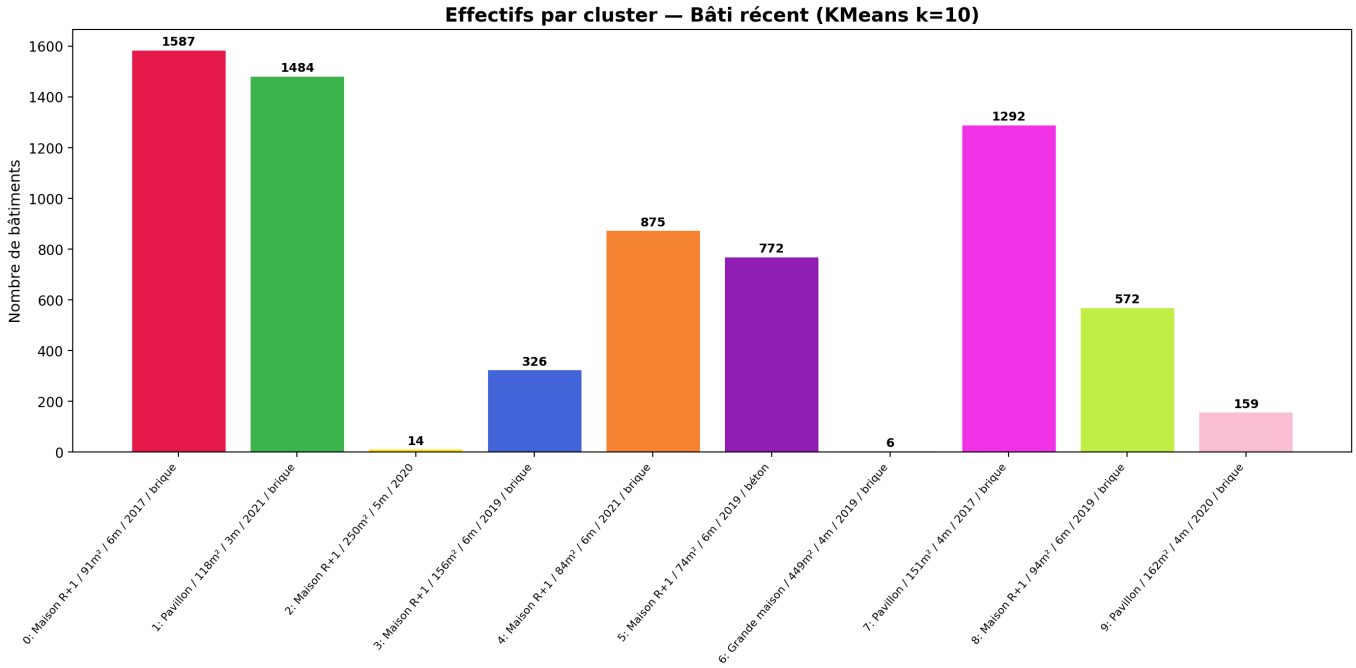

2. Distribution par année de construction

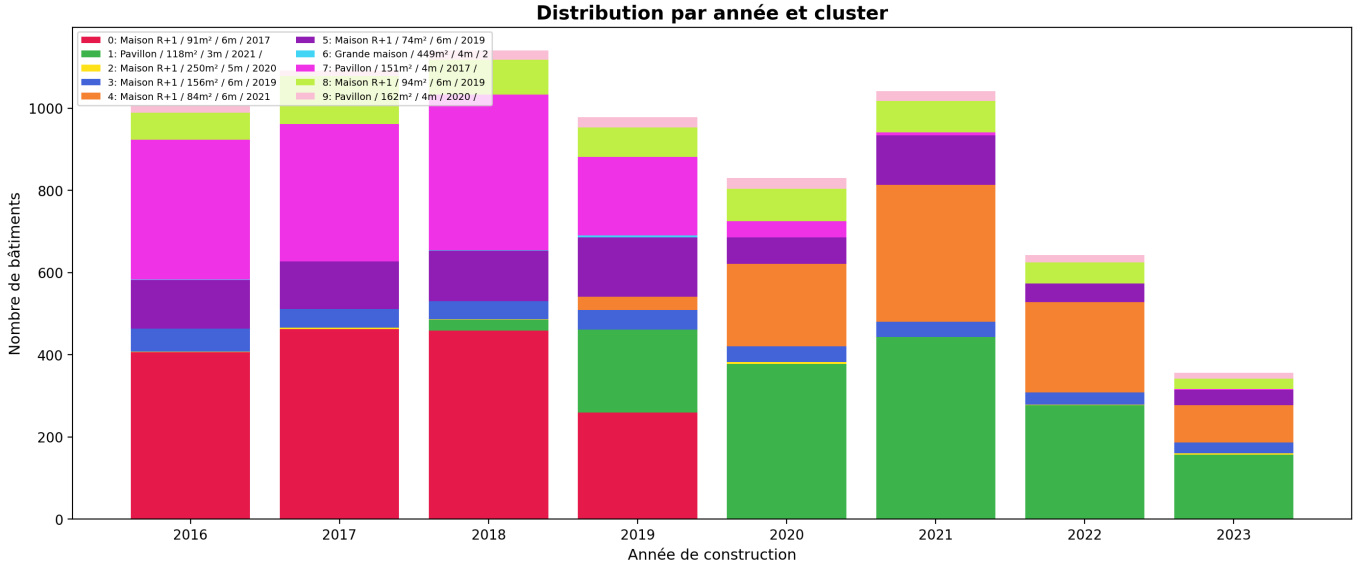

3. Distributions surface et hauteur

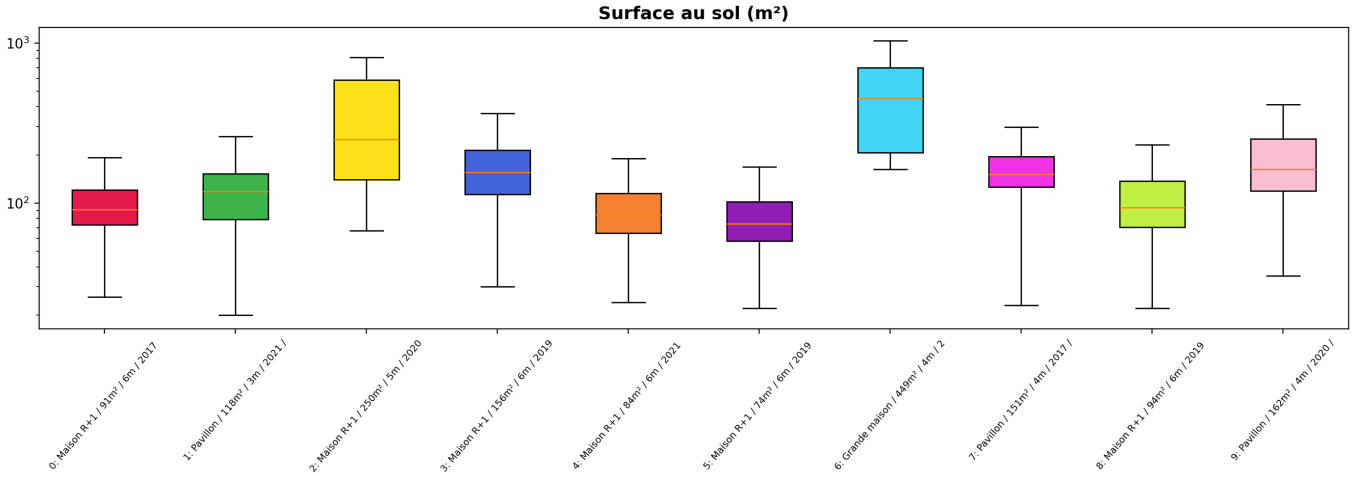

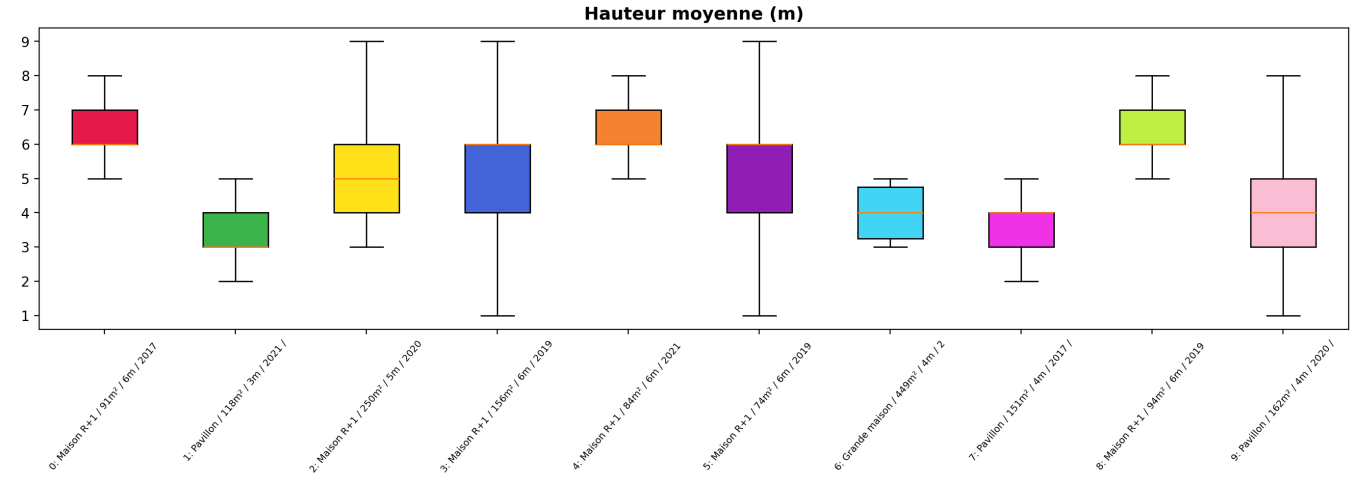

4. Analyse parcellaire

Jointure spatiale des 11 465 parcelles classées (sur 307 290 parcelles métropole) aux bâtiments clusterisés. Chaque parcelle prend le cluster du bâtiment dominant (plus grande emprise au sol).

Indicateurs parcellaires par cluster

Cl.	Nom	Parcelles	Surf. parc.	CES méd.	Bât./parc.
0	Maison R+1 / 91m² / 6m / 2017 /	2 473	261 m²	40.4%	1.0
1	Pavillon / 118m² / 3m / 2021 / b	2 277	422 m²	29.2%	1.0
2	Maison R+1 / 250m² / 5m / 2020	40	398 m²	43.6%	1.0
3	Maison R+1 / 156m² / 6m / 2019 /	680	294 m²	59.4%	1.0
4	Maison R+1 / 84m² / 6m / 2021 /	1 483	215 m²	47.9%	1.0
5	Maison R+1 / 74m² / 6m / 2019 /	1 227	221 m²	47.9%	1.0
6	Grande maison / 449m² / 4m / 201	22	230 m²	88.2%	1.0
7	Pavillon / 151m² / 4m / 2017 / b	1 874	525 m²	29.5%	1.0
8	Maison R+1 / 94m² / 6m / 2019 /	995	243 m²	42.5%	1.0
9	Pavillon / 162m² / 4m / 2020 / b	394	358 m²	44.6%	1.0

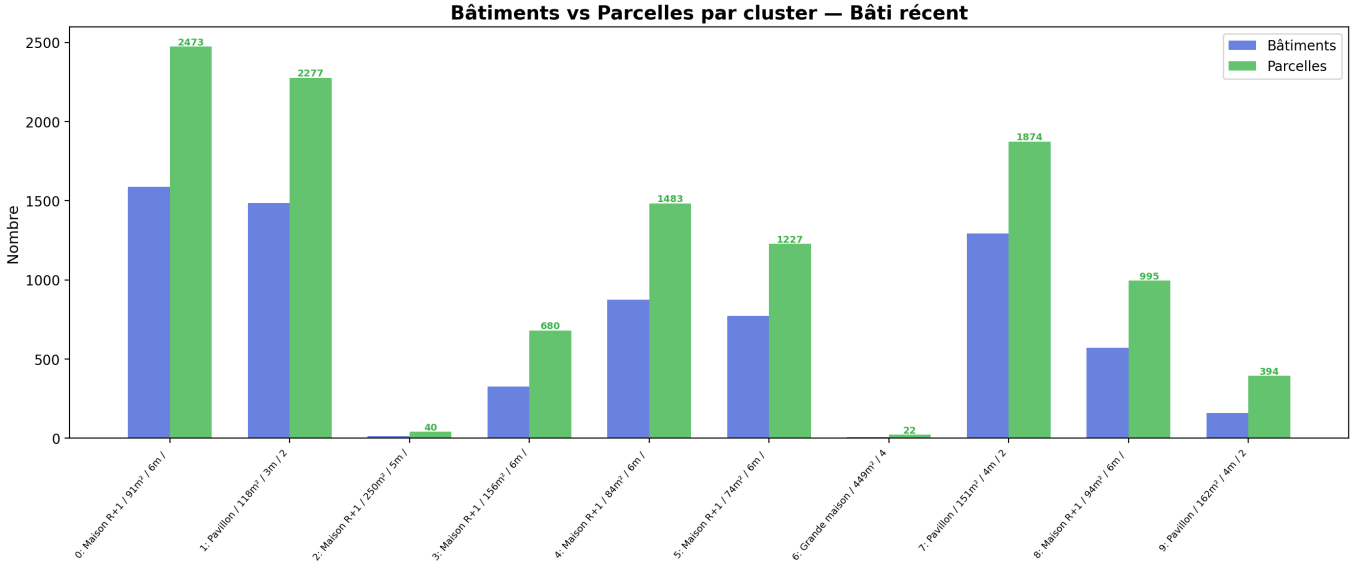
Bâtiments vs Parcelles par cluster — Bâti récent
Nombre
Bâtiments
Parcelles
0
500
1000
1500
2000
2500
2473
2277
40
680
1483
1227
22
1874
995
394
0: Maison R+1 / 91m² / 6m /
1: Pavillon / 118m² / 3m / 2
2: Maison R+1 / 250m² / 5m /
3: Maison R+1 / 156m² / 6m /
4: Maison R+1 / 84m² / 6m /
5: Maison R+1 / 74m² / 6m /
6: Grande maison / 449m² / 4
7: Pavillon / 151m² / 4m / 2
8: Maison R+1 / 94m² / 6m /
9: Pavillon / 162m² / 4m / 2

CES par cluster

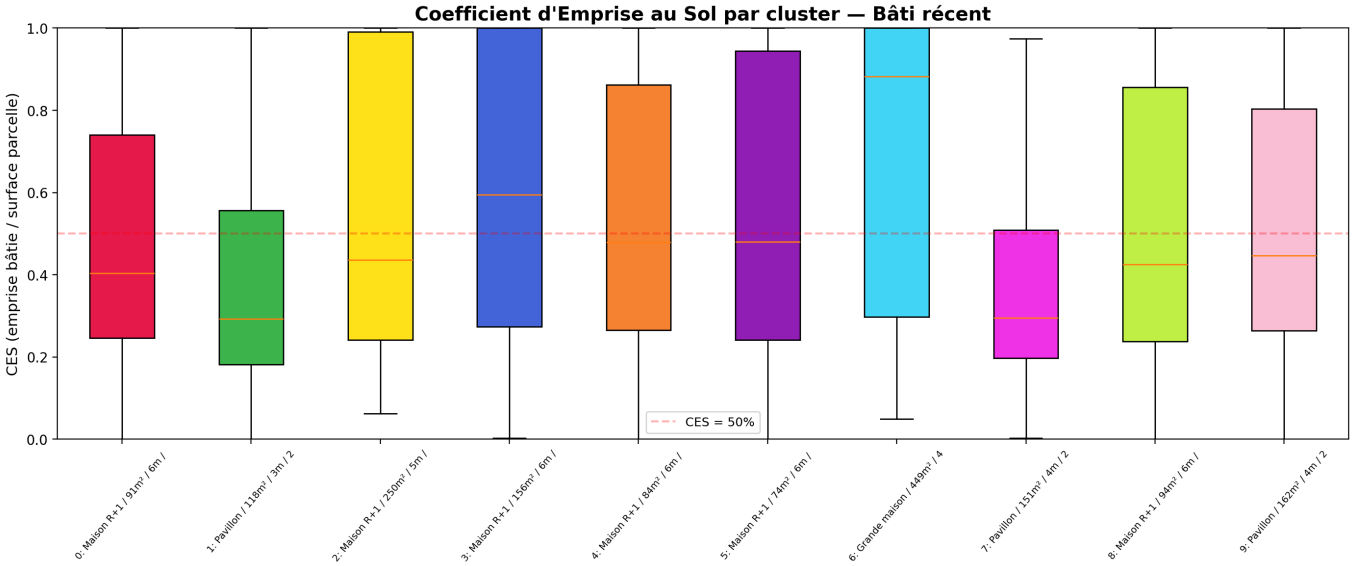

Le CES (Coefficient d'Emprise au Sol) mesure le rapport entre l'emprise bâtie et la surface de la parcelle. Un CES élevé indique une parcelle densément bâtie, un CES faible une parcelle avec jardin.

5. Description des clusters

■ **Cluster 0** — Maison R+1 / 91m² / 6m / 2017 / brique (1587 bât., 22.4%) — BRIQUES — Années : 2016: 406, 2017: 463, 2018: 459

■ **Cluster 1** — Pavillon / 118m² / 3m / 2021 / brique (1484 bât., 20.9%) — BRIQUES — Années : 2018: 26, 2019: 202, 2020: 378

■ **Cluster 2** — Maison R+1 / 250m² / 5m / 2020 (14 bât., 0.2%) — INDETERMINE — Années : 2016: 2, 2017: 3, 2018: 1

■ **Cluster 3** — Maison R+1 / 156m² / 6m / 2019 / brique (326 bât., 4.6%) — BRIQUES — Années : 2016: 56, 2017: 45, 2018: 44

■ **Cluster 4** — Maison R+1 / 84m² / 6m / 2021 / brique (875 bât., 12.3%) — BRIQUES — Années : 2019: 32, 2020: 200, 2021: 334

■ **Cluster 5** — Maison R+1 / 74m² / 6m / 2019 / béton (772 bât., 10.9%) — BETON — Années : 2016: 118, 2017: 116, 2018: 124

■ **Cluster 6** — Grande maison / 449m² / 4m / 2019 / brique (6 bât., 0.1%) — BRIQUES — Années : 2016: 1, 2018: 1, 2019: 4

■ **Cluster 7** — Pavillon / 151m² / 4m / 2017 / brique (1292 bât., 18.2%) — BRIQUES — Années : 2016: 340, 2017: 334, 2018: 378

■ **Cluster 8** — Maison R+1 / 94m² / 6m / 2019 / brique (572 bât., 8.1%) — BRIQUES — Années : 2016: 66, 2017: 118, 2018: 85

■ **Cluster 9** — Pavillon / 162m² / 4m / 2020 / brique (159 bât., 2.2%) — BRIQUES — Années : 2016: 18, 2017: 12, 2018: 22

6. Analyse et conclusions

Caractéristiques du bâti récent :

• Domination de la brique comme matériau de construction (>70%)
• Deux morphologies : pavillons plain-pied (3-4m) et maisons R+1 (5-7m)
• Surface médiane de 74 à 162 m² selon les types
• Le béton apparaît dans un cluster spécifique (cluster 5, 772 bâtiments)
• Pic de construction en 2017-2018, décélération à partir de 2020
• Les très grandes maisons (>200m²) sont marginales (<1%)

Pistes suivantes :

• Croiser avec les données DVF pour analyser les prix du bâti récent
• Comparer la localisation du bâti récent avec le PLU (zones AU)
• Analyser la performance énergétique (DPE) par cluster