Clustering v3 — Résidentiel individuel

Bordeaux Métropole — 28 communes

150 119 bâtiments — résidentiel individuel nb_logements < 4

Algorithme : KMeans k=15 — 11 features (6 numériques + 5 catégorielles)

Source : BDNB millésime 2025-07-a — Date : mars 2026

Ce rapport analyse les typologies du bâti résidentiel individuel (moins de 4 logements) sur Bordeaux Métropole. Les bâtiments tertiaires, collectifs, dépendances et à usage inconnu sont exclus. Les cartes interactives sont disponibles sur la carte web associée.

1. Effectifs par cluster

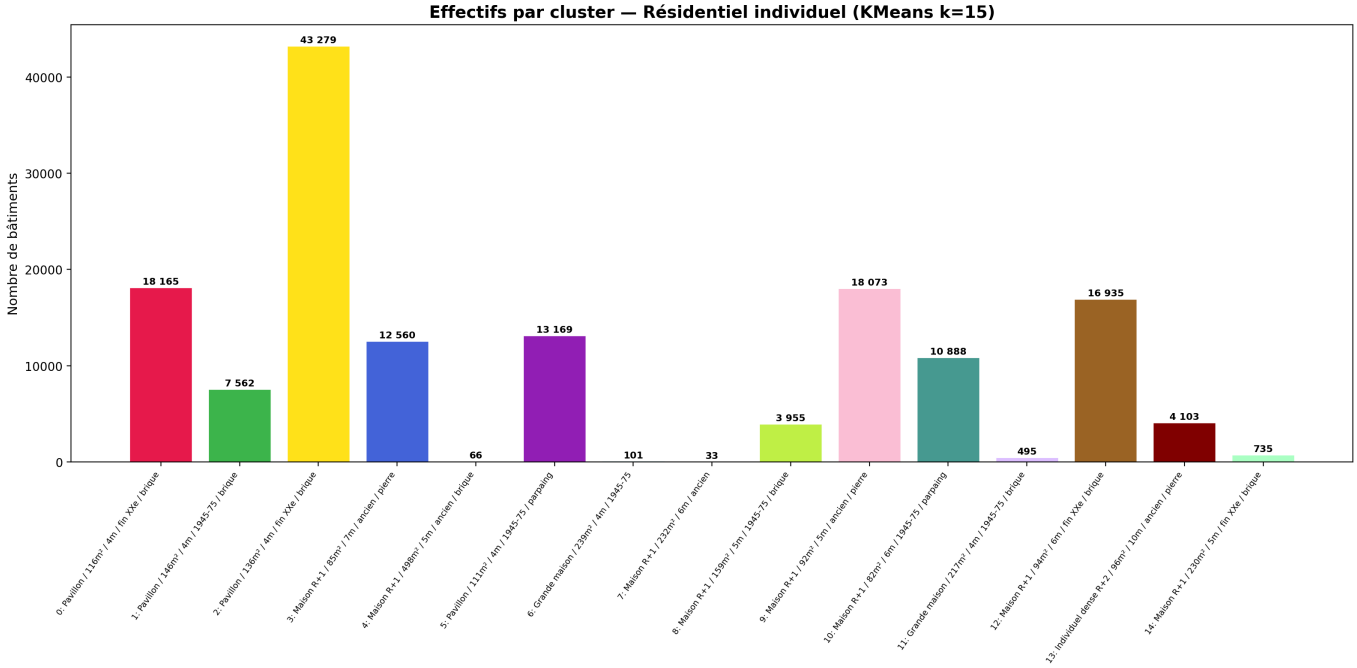

2. Profil synthétique des 15 clusters

Cl.	Nom	N	%	Surf.	Haut.	Niv.	Année	Mat. murs
0	Pavillon / 116m² / 4m / fin XXe	18165	12.1	116	4.0	2	1983	BRIQUES
1	Pavillon / 146m² / 4m / 1945-75	7562	5.0	146	4.0	1	1973	BRIQUES
2	Pavillon / 136m² / 4m / fin XXe	43279	28.8	136	4.0	1	1985	BRIQUES
3	Maison R+1 / 85m² / 7m / ancien	12560	8.4	85	7.0	2	1900	PIERRE
4	Maison R+1 / 498m² / 5m / ancien	66	0.0	498	5.0	1	1932	BRIQUES
5	Pavillon / 111m² / 4m / 1945-75	13169	8.8	111	4.0	1	1962	AGGLOMERE
6	Grande maison / 239m² / 4m / 194	101	0.1	239	4.0	1	1970	INDETERMINE
7	Maison R+1 / 232m² / 6m / ancien	33	0.0	232	6.0	2	1900	INDETERMINE
8	Maison R+1 / 159m² / 5m / 1945-7	3955	2.6	159	5.0	1	1974	BRIQUES
9	Maison R+1 / 92m² / 5m / ancien	18073	12.0	92	5.0	1	1900	PIERRE
10	Maison R+1 / 82m² / 6m / 1945-75	10888	7.3	82	6.0	2	1962	AGGLOMERE
11	Grande maison / 217m² / 4m / 194	495	0.3	217	4.0	1	1960	BRIQUES
12	Maison R+1 / 94m² / 6m / fin XXe	16935	11.3	94	6.0	2	1990	BRIQUES
13	Individuel dense R+2 / 96m² / 10	4103	2.7	96	10.0	3	1900	PIERRE
14	Maison R+1 / 230m² / 5m / fin XX	735	0.5	230	5.0	2	1993	BRIQUES

3. Distributions surface et hauteur

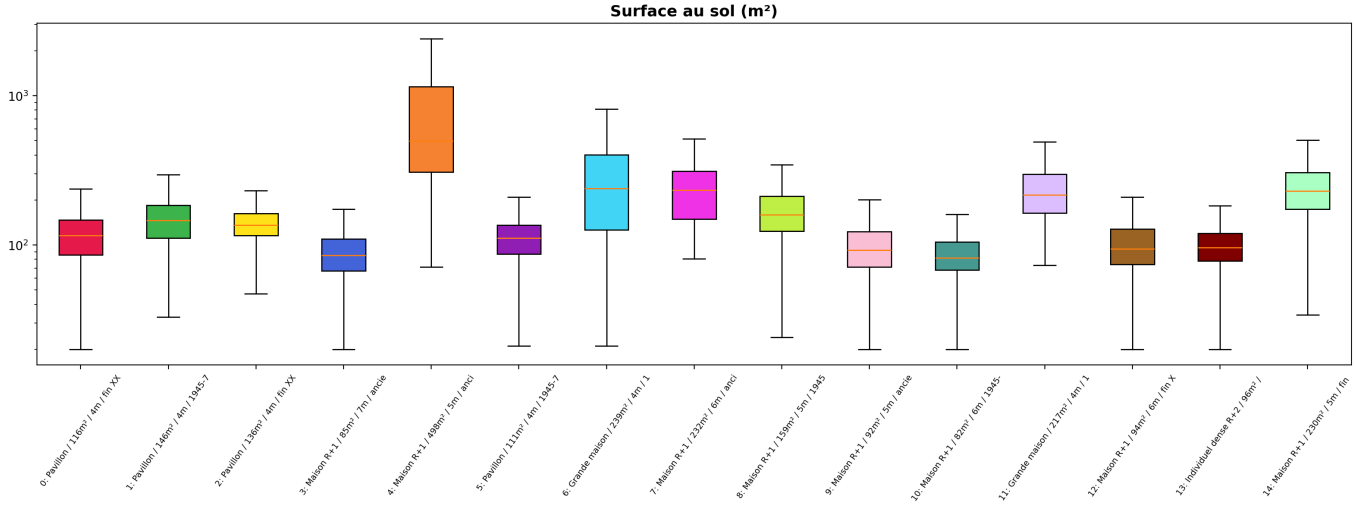

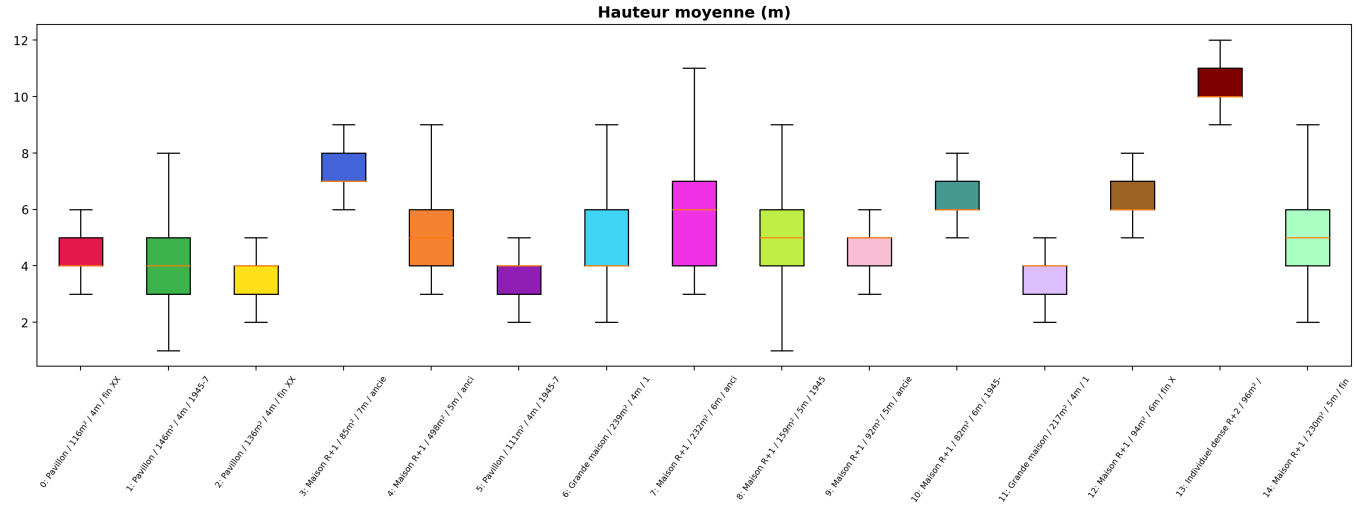

4. Matériaux de murs par cluster

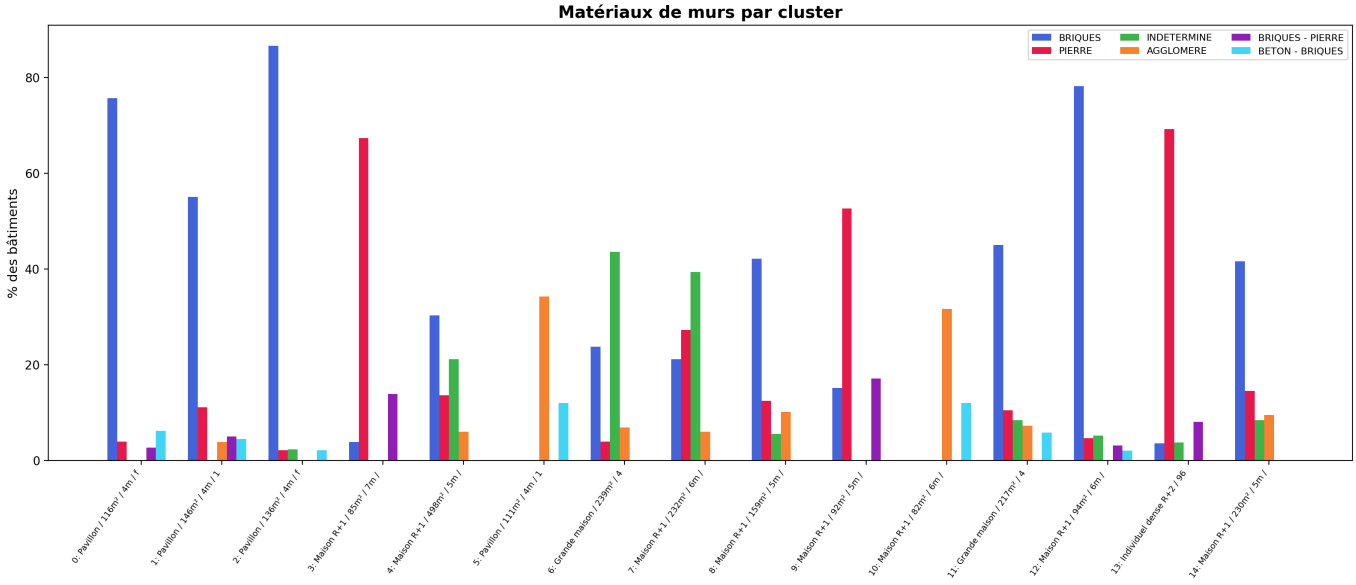

5. Description des clusters

- **Cluster 0** — Pavillon / 116m² / 4m / fin XXe / brique (18 165 bât. 12.1%) — 116 m² 4.0 m 1983 BRIQUES
- **Cluster 1** — Pavillon / 146m² / 4m / 1945-75 / brique (7 562 bât. 5.0%) — 146 m² 4.0 m 1973 BRIQUES
- **Cluster 2** — Pavillon / 136m² / 4m / fin XXe / brique (43 279 bât. 28.8%) — 136 m² 4.0 m 1985 BRIQUES
- **Cluster 3** — Maison R+1 / 85m² / 7m / ancien / pierre (12 560 bât. 8.4%) — 85 m² 7.0 m 1900 PIERRE
- **Cluster 4** — Maison R+1 / 498m² / 5m / ancien / brique (66 bât. 0.0%) — 498 m² 5.0 m 1932 BRIQUES
- **Cluster 5** — Pavillon / 111m² / 4m / 1945-75 / parpaing (13 169 bât. 8.8%) — 111 m² 4.0 m 1962 AGGLOMERE
- **Cluster 6** — Grande maison / 239m² / 4m / 1945-75 (101 bât. 0.1%) — 239 m² 4.0 m 1970 INDETERMINE
- **Cluster 7** — Maison R+1 / 232m² / 6m / ancien (33 bât. 0.0%) — 232 m² 6.0 m 1900 INDETERMINE
- **Cluster 8** — Maison R+1 / 159m² / 5m / 1945-75 / brique (3 955 bât. 2.6%) — 159 m² 5.0 m 1974 BRIQUES
- **Cluster 9** — Maison R+1 / 92m² / 5m / ancien / pierre (18 073 bât. 12.0%) — 92 m² 5.0 m 1900 PIERRE
- **Cluster 10** — Maison R+1 / 82m² / 6m / 1945-75 / parpaing (10 888 bât. 7.3%) — 82 m² 6.0 m 1962 AGGLOMERE
- **Cluster 11** — Grande maison / 217m² / 4m / 1945-75 / brique (495 bât. 0.3%) — 217 m² 4.0 m 1960 BRIQUES
- **Cluster 12** — Maison R+1 / 94m² / 6m / fin XXe / brique (16 935 bât. 11.3%) — 94 m² 6.0 m 1990 BRIQUES
- **Cluster 13** — Individuel dense R+2 / 96m² / 10m / ancien / pierre (4 103 bât. 2.7%) — 96 m² 10.0 m 1900 PIERRE
- **Cluster 14** — Maison R+1 / 230m² / 5m / fin XXe / brique (735 bât. 0.5%) — 230 m² 5.0 m 1993 BRIQUES

6. Conclusions

• 15 typologies clairement différenciées par surface, hauteur, période et matériaux
• Les pavillons (clusters 0, 1, 2, 5) représentent ~55% du stock résidentiel individuel
• Le bâti ancien en pierre (clusters 3, 9, 13) se distingue nettement du pavillonnaire récent en brique
• Les maisons R+1 (clusters 8, 10, 12, 19) forment un gradient par période et matériau
• L'individuel dense R+2 (cluster 13, pierre, ancien) correspond au centre historique bordelais

Pistes d'amélioration :

• Enrichir avec les features DVF (prix m²) et INSEE (revenus)
• Calculer le Moran's I (cohérence spatiale) par cluster
• Tester un clustering séparé pour les collectifs (nb_logements >= 4)